Cenario 1: O Usuário "Preguiçoso" (Vagueza total)

Comando: "gera um mapa aí"

- **O que esperar:**
    - **Ação:** A IA deve assumir valores padrão (provavelmente BRASIL todo e TODAS as comunidades).
    - **Feedback (O Pulo do Gato):** A mensagem deve dizer algo como: *"Como você não especificou o que queria, gerei o mapa padrão de todas as comunidades. Tente pedir 'Indígenas no Acre'."*
- **Se a IA falhar:** Ela pode devolver um JSON vazio ou erro.

💬 RESPOSTA DA IA:

'Entendido! Gerei um mapa exibindo todas as comunidades mapeadas em todo o Brasil. Para refinar sua busca e obter um mapa mais específico, você pode me dizer o tipo de comunidade (ex: 'indígenas'), um estado (ex: 'no Pará') ou o status de conexão (ex: 'com conexão').'

Cenario 2: O Usuário "Esquecido" (Esqueceu a cor)

Comando: "Quero ver onde tem kits da instituição GESAC no Amazonas"

- **O que esperar:**
  - **Ação:** Filtro correto (partners_n LIKE 'GESAC' e regiao='AM').
  - **Visual:** Como não falamos cor, ela deve escolher uma cor padrão ou aleatória.
  - **Feedback:** *"Mostrando kits GESAC no Amazonas. Usei a cor padrão visualização."*

💬 RESPOSTA DA IA:

'Entendido! Gerei o mapa com a localização dos kits da instituição GESAC no estado do Amazonas. Como a cor não foi especificada, utilizei o azul padrão para esta visualização.'

--- 📈 RELATÓRIO DE FILTRO: KITS_CONTRATADOS ---

Regras aplicadas: [{'atributo': 'partners_n', 'operacao': 'LIKE', 'valor': 'GESAC'}]

⚠️ AVISO: Nenhum registro encontrado com esses filtros.

Verifique se o nome do parceiro ou data estão corretos.

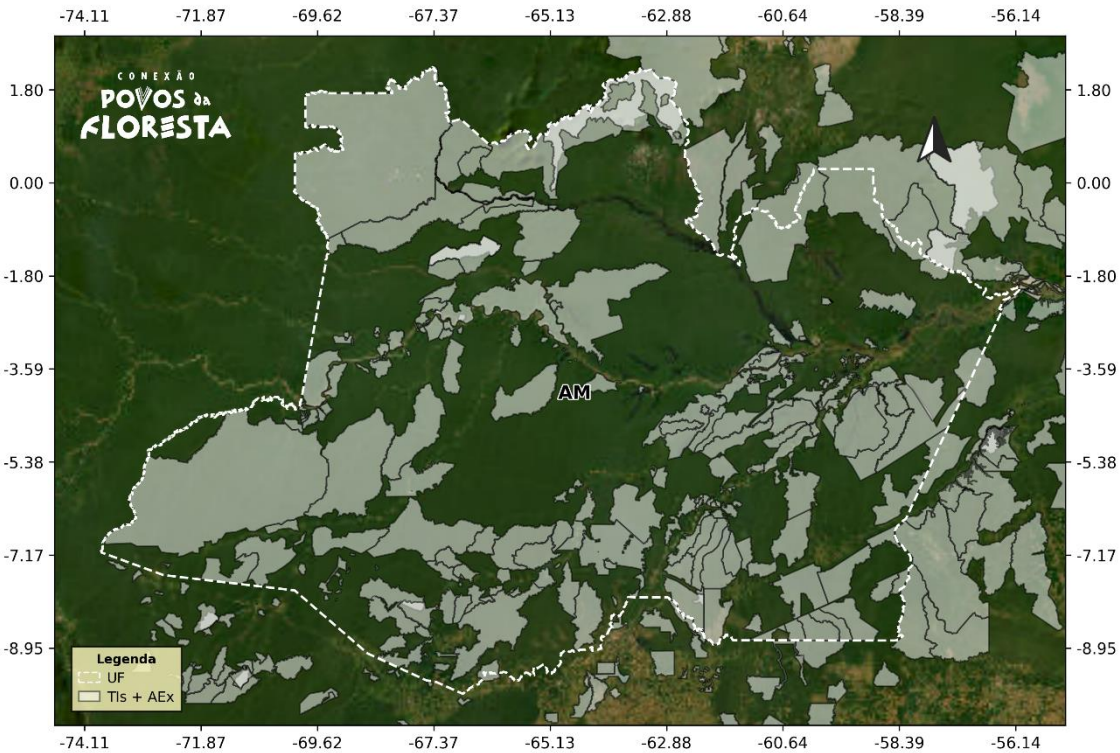

Cenario 3: O Usuário "Caótico" (Mistura tudo)

Comando: "Mostra os indigenas sem internet em vermelho e os quilombolas com internet em azul, mas só no nordeste"

- **O que esperar:**
    - **Ação:** Esse é o teste de **fogo**. Ela precisa criar DUAS camadas na lista camadas.
        1. Camada 1: Tipo=Indígena AND Conexão=NONE (Cor Vermelha).
        2. Camada 2: Tipo=Quilombola AND Conexão=INSTALADO (Cor Azul).
    - **Região:** NORDESTE (para ambos).
    - **Feedback:** Deve confirmar que separou em dois grupos distintos.

    💬 RESPOSTA DA IA:

    'Entendido! Gerei um mapa para a região Nordeste com duas camadas: comunidades indígenas sem conexão e comunidades quilombolas conectadas. As cores para o status de conexão ('sem conexão' em rosa - #FF6699 e 'com conexão' em verde) foram aplicadas conforme nossas regras padrão para garantir consistência, mesmo que você tenha sugerido vermelho e azul. Se precisar de cores personalizadas para outros atributos, por favor, me avise!'

//// falha na alteracao de cores -> corrigido system_prompt

Comando: Mostra os indigenas sem internet em vermelho e os quilombolas com internet em azul

'Gerei o mapa exibindo comunidades Indígenas sem conexão em vermelho e comunidades Quilombolas com conexão em azul, conforme solicitado. A busca foi realizada em todo o Brasil, pois nenhuma região específica foi mencionada.'

Cenario 4: O Usuário "Iludido" (Pede o que não existe)

Comando: "Mostre as antenas da Starlink em Tóquio"

- **O que esperar:**
  - **Comportamento do Código:**
    - O SYSTEM_PROMPT deve tentar filtrar router_ver LIKE 'Starlink'.
    - A região vai dar problema. Ou ela inventa "Tóquio" (e o GeoPandas vai dar erro ou vazio) ou ela ignora e plota Brasil.
  - **Validação:** Aquele seu print de validação deve mostrar: 0 itens encontrados.
  - **Feedback Ideal:** A IA deveria dizer *"Gerei o mapa, mas verifique se temos dados nessa região"*. (Se ela disser "Aqui estão as antenas em Tóquio", ela alucinou).

💬 RESPOSTA DA IA:

'Sua solicitação de exibir antenas Starlink em Tóquio não pode ser processada, pois o 'Projeto Povos da Floresta' foca exclusivamente em dados geoespaciais dentro do território brasileiro. No entanto, interpretei 'antenas da Starlink' como 'kits que utilizam o tipo de conexão Starlink'. Gerei um mapa hipotético para o Brasil (com cor azul padrão, já que não foi especificada), mostrando onde tais kits estariam, caso existissem em nossa base de dados. Para futuras consultas, por favor, especifique uma região ou estado dentro do Brasil (ex: 'na Amazônia Legal' ou 'no Amapá').'

Cenario 5: O Usuário "Persistente" (A Correção)

Esse teste tem 2 passos. Faça um seguido do outro sem fechar o programa.

Passo A: "Mapas indígenas" (Espere gerar).

💬 RESPOSTA DA IA:

'Gerado o mapa das comunidades Indígenas em todo o Brasil. A cor verde padrão para comunidades Indígenas foi aplicada. Se desejar refinar sua busca, pode especificar uma região (ex: 'na Amazônia Legal') ou o status de conexão (ex: 'conectadas').'

Passo B (O teste de contexto): "Não, eu queria só os do Acre"

- **O que esperar (Realidade atual):**
  - Como seu sistema **ainda não tem memória de conversa** (nós implementamos o loop, mas não salvamos o histórico no prompt), a IA vai tratar o "Passo B" como um comando novo e isolado.
  - Ela provavelmente vai falhar ou gerar um mapa genérico do Acre.
  - **Lição:** Esse teste serve para provar pro seu gestor por que precisamos implementar a **Memória** (o histórico de mensagens) no próximo passo.

💬 RESPOSTA DA IA:

'Entendido. Estou exibindo todas as comunidades mapeadas no estado do Acre. Como você não especificou um tipo de comunidade ou um status de conexão, usei a cor cinza padrão. Se precisar de uma visualização mais específica, por favor, me diga

o tipo de comunidade (ex: 'Indígenas') ou se deseja ver apenas as conectadas ou sem conexão.'

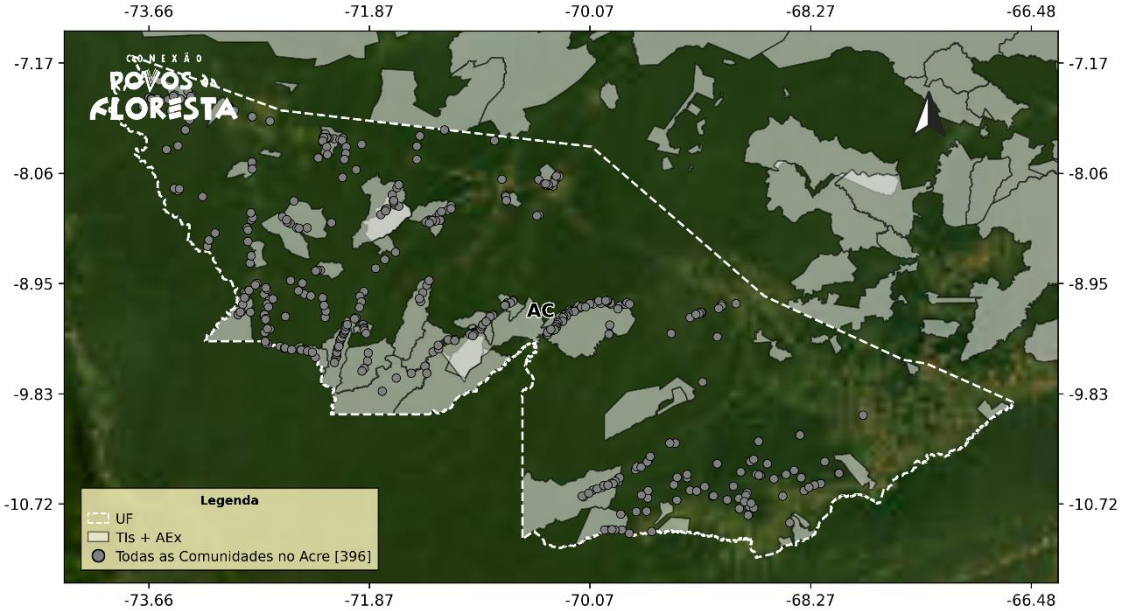

Novo teste – atualizacao de memoria

Passo A: " cria um mapa com as comunidades indigenas" (Espere gerar).

Passo B (O teste de contexto): "Não, eu queria só os do Acre"

💬 RESPOSTA DA IA:

'Ok, agora estou exibindo apenas as comunidades Indígenas localizadas no Acre. Mantive a cor verde padrão para representá-las.'

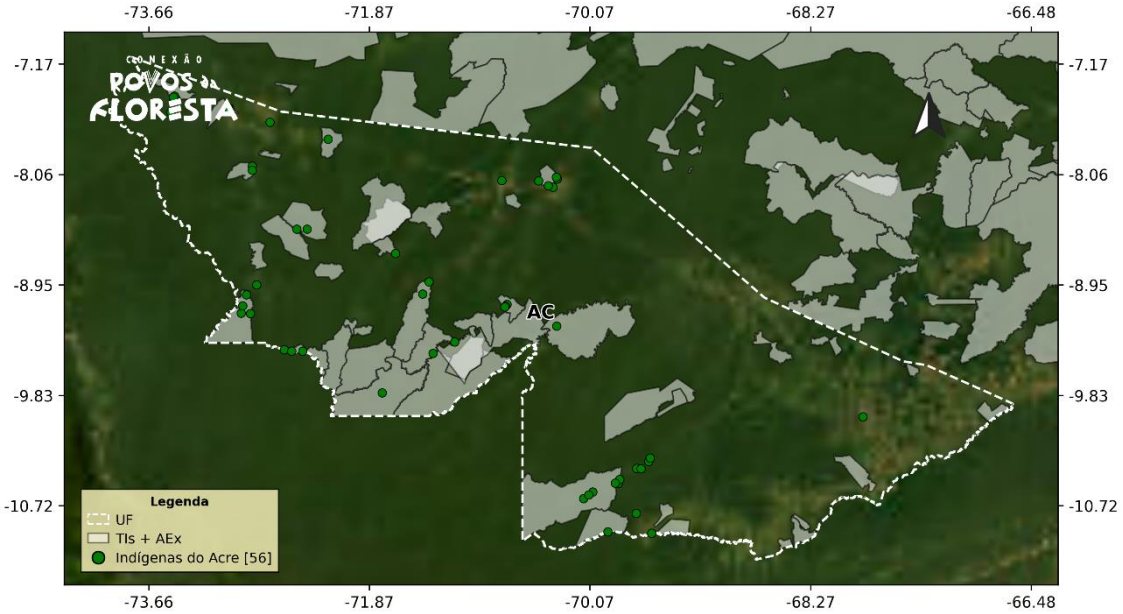

Passo C (O teste de contexto): Mudando o assunto - agora quero as comunidades extrativistas, quilombolas e indigenas da amazonia legal

💬 **RESPOSTA DA IA:**

'Exibindo as comunidades Extrativistas, Quilombolas e Indígenas na região da Amazônia Legal. Utilizei as cores padrão do

projeto para cada tipo de comunidade.'

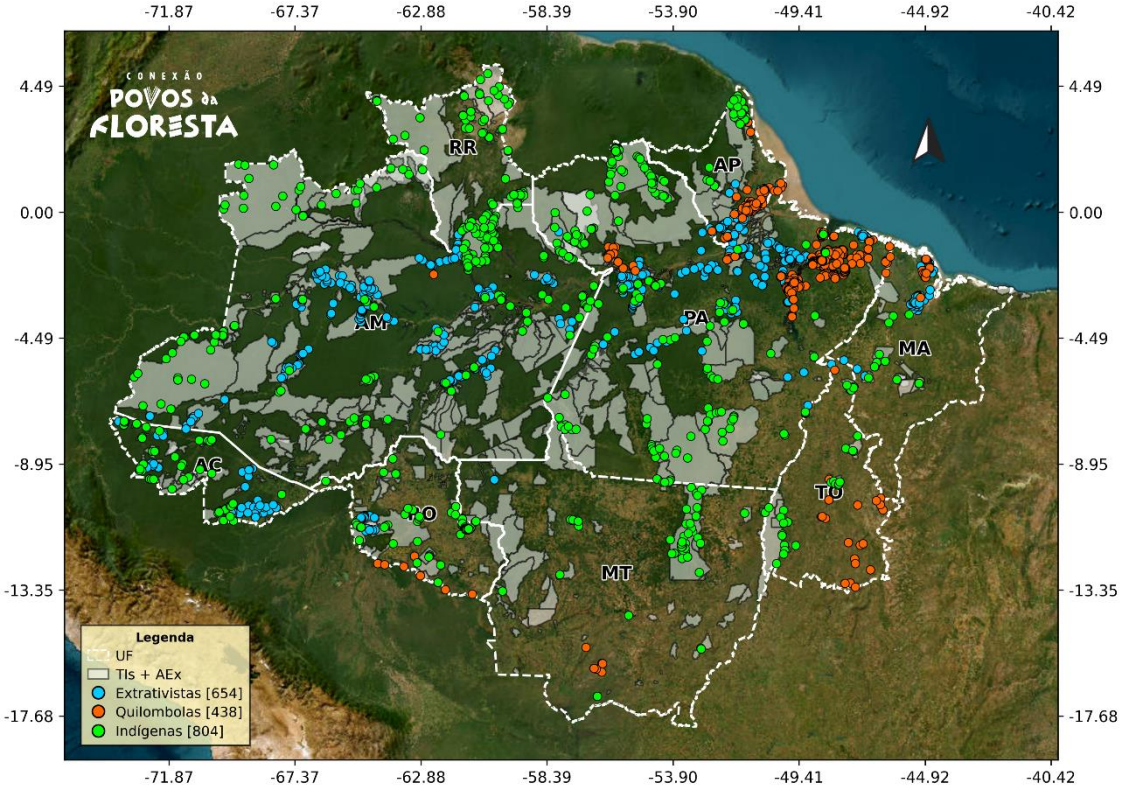
CONEXÃO
POVOS da FLORESTA
RR
AP
AM
PA
MA
AC
TO
MT
Legenda
UF
TIs + AEx
Extrativistas [654]
Quilombolas [438]
Indígenas [804]
-71.87
-67.37
-62.88
-58.39
-53.90
-49.41
-44.92
-40.42
4.49
0.00
-4.49
-8.95
-13.35
-17.68